Инструкция

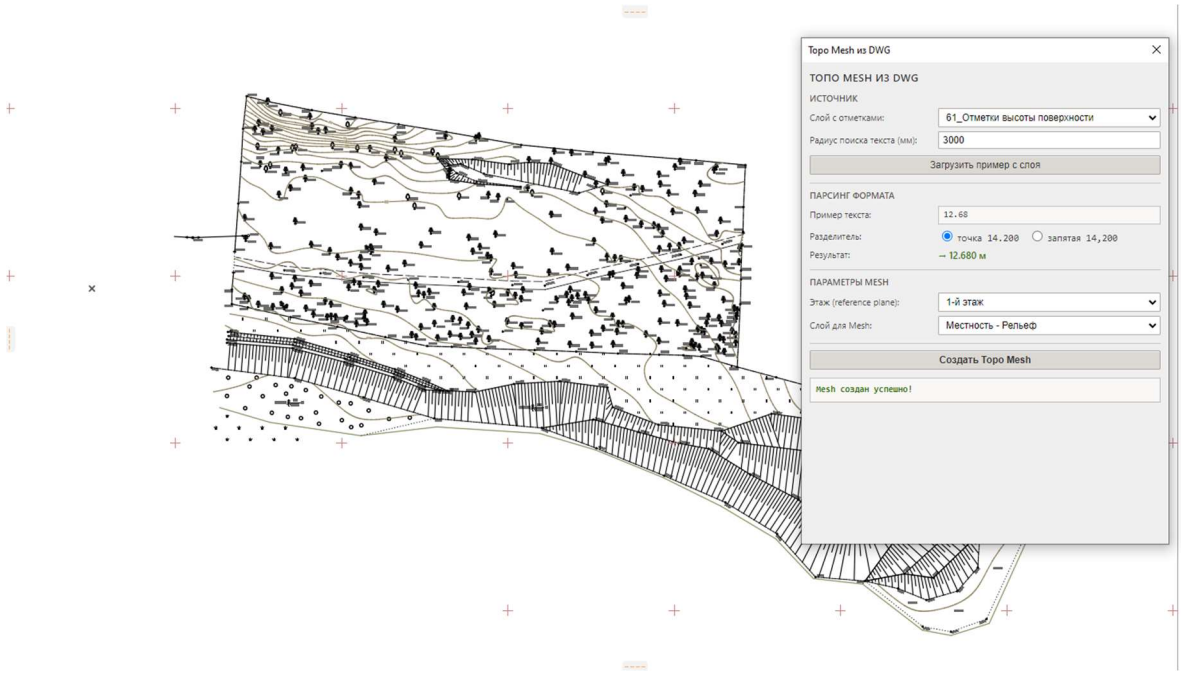

• Поддержка форматов:
14.200
14,200

• Настройка радиуса поиска текста
• Автоматическое определение границы Mesh
• Выбор:

- слоя источника
- слоя Mesh
- выбора этажа для размещения 3D Сетки

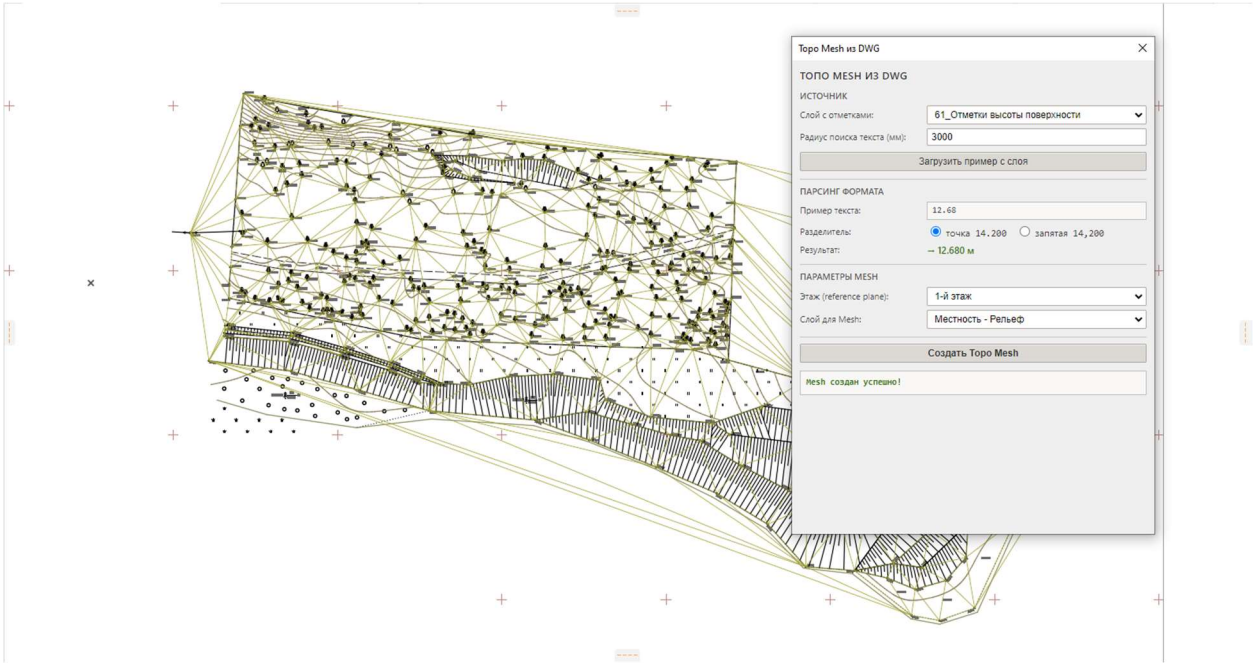

Как это работает

1. Импортируйте DWG с отметками высот.
2. Декомпозируйте и убедитесь что импортируются слои из DWG
3. Убедитесь, что отметки представлены текстовыми элементами.
4. Откройте панель DWG-mesh.
5. Выберите слой с отметками.
6. Нажмите Создать Topo Mesh.

Плагин:

- • находит текстовые отметки
- • преобразует их в координаты высоты
- • создаёт Archicad Mesh

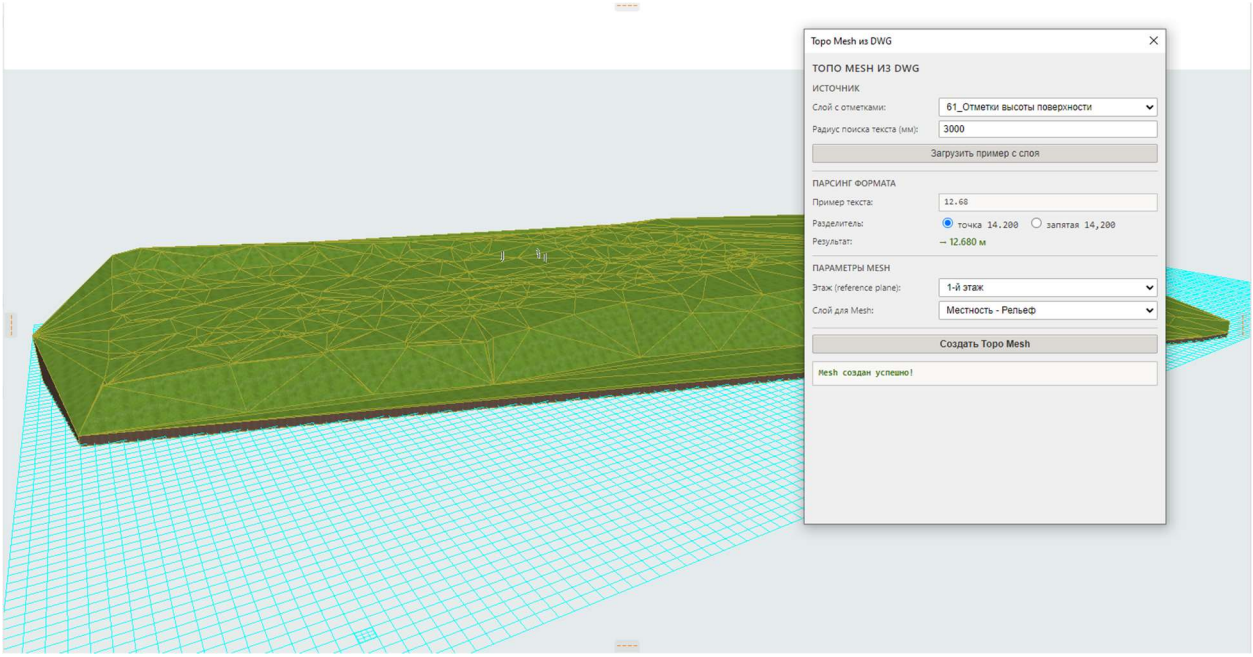

Интерфейс

Панель содержит настройки:

Параметр	Описание
Слой с отметками	Слой, где находятся текстовые высоты
Радиус поиска	Радиус поиска текста возле точки
Разделитель	Точка или запятая
Этаж	Выбор этажа для размещения 3D Сетки
Слой Mesh	Слой куда будет создан Mesh

Установка

1. Распакуйте архив
2. Поместите файл DWG-mesh_AC27.apx
3. в папку:
4. Archicad/Add-Ons
5. Перезапустите Archicad.
6. После этого панель появится в меню аддонов.